BUKU PANDUAN

Dashboard Koperasi

Desa / Kelurahan Merah Putih Sulawesi Tenggara

Panduan lengkap tata cara penggunaan aplikasi pemetaan, pemantauan, dan pengelolaan data koperasi berbasis web — untuk operator, administrator, dan pengguna umum.

v1.0
VERSI

- Peta Interaktif Leaflet.js
- Dashboard Statistik
- API Kemenkop
- Kelola Basis Data
- Export Excel
- Multi-Basemap

9
BAB

4	9	28	4+	API
HALAMAN UTAMA	BAB PANDUAN	SLIDE PRESENTASI	JENIS BASEMAP	INTEGRASI KEMENKOP

DISUSUN OLEH
@m45y
LATSAR CPNS 2026
Golongan III · Angkatan I

2026
TAHUN TERBIT

BUKU PANDUAN PENGGUNAAN

Dashboard Koperasi
Desa/Kelurahan Merah Putih
Sulawesi Tenggara

Panduan lengkap untuk operator, administrator, dan pengguna umum

Dibuat oleh: @m45y
Untuk LATSAR CPNS 2026 | GOL III, ANGKATAN I

Versi Dokumen: 1.0 · Tahun 2026

Daftar Isi

BAB 1 — Pendahuluan Tentang Aplikasi, Tujuan, Pengguna, Teknologi

BAB 2 — Navigasi Umum Struktur Halaman, Sidebar, Layout

BAB 3 — Halaman Peta Persebaran (index.html) Peta, Marker, Panel Info, Filter, Tabel

BAB 4 — Dashboard Statistik (statistik.html) KPI, Grafik, Filter Wilayah

BAB 5 — Login Administrator (login.html) Autentikasi & Hak Akses

BAB 6 — Kelola Basis Data (database.html) Tambah, Edit, Hapus Data, Upload Foto

BAB 7 — Sinkronisasi API Kemenkop Integrasi Data Nasional

BAB 8 — Tips & Troubleshooting Solusi Masalah Umum & Tips Optimal

BAB 1 — Pendahuluan

1.1 Tentang Aplikasi

Dashboard Koperasi Desa/Kelurahan Merah Putih Sulawesi Tenggara adalah aplikasi berbasis web yang dirancang untuk memetakan, memantau, dan mengelola data koperasi di wilayah Sulawesi Tenggara. Dikembangkan sebagai bagian dari program Latsar CPNS 2026 Golongan III, Angkatan I.

Aplikasi ini menyediakan antarmuka peta interaktif, dashboard statistik, serta modul manajemen data yang terintegrasi dengan Google Sheets sebagai basis data utama dan API Kemenkop sebagai sumber data sinkronisasi.

1.2 Tujuan & Fitur Utama

- Memetakan sebaran geografis koperasi desa/kelurahan secara visual dan interaktif.
- Memudahkan monitoring status operasional dan tingkat kesehatan koperasi.
- Mendukung pengelolaan data koperasi secara terpusat oleh administrator.
- Menyediakan dashboard statistik untuk analisis dan pelaporan.
- Mengintegrasikan data dengan sistem nasional API Kemenkop.

1.3 Jenis Pengguna

Jenis Pengguna	Hak Akses
Pengguna Umum (Guest)	Lihat peta, info koperasi, statistik, ekspor Excel
Administrator	Semua akses guest + tambah/edit/hapus data, sinkronisasi API

1.4 Teknologi

Komponen	Teknologi
Peta Interaktif	Leaflet.js + OpenStreetMap / Google Satellite
Grafik & Statistik	Chart.js
Basis Data	Google Sheets via Google Apps Script Web App
Export Data	SheetJS (XLSX)
Sinkronisasi Nasional	API Kemenkop (merahputih.kop.id)

BAB 2 — Navigasi Umum

2.1 Struktur Layout Aplikasi

Setiap halaman menggunakan layout konsisten: Header (atas), Sidebar kiri, dan Area Konten kanan. Sidebar memuat menu navigasi ke 4 halaman utama dan dapat dikecilkan dengan tombol ≡ di header.

Halaman	Fungsi
index.html	Peta persebaran koperasi + tabel data
statistik.html	Dashboard KPI dan grafik statistik
database.html	Manajemen data koperasi (Admin only)
login.html	Autentikasi administrator

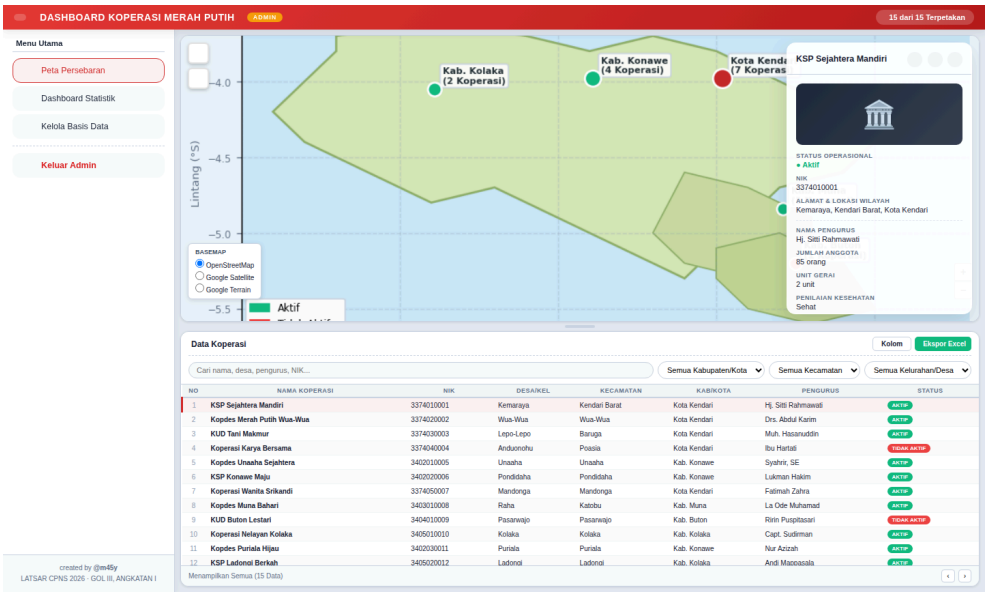

Gambar: Tampilan utama aplikasi: Sidebar navigasi, peta Sulawesi Tenggara, Panel Info koperasi aktif, dan tabel data lengkap

2.2 Header Aplikasi

Header berwarna merah (di bagian atas) menampilkan: tombol hamburger ≡ untuk buka/tutup sidebar, nama aplikasi, badge ADMIN (jika login), dan tombol statistik di kanan yang menampilkan jumlah koperasi terpetakan dan berfungsi sebagai tombol refresh data.

BAB 3 — Halaman Peta Persebaran

3.1 Peta Interaktif

Peta menampilkan seluruh koperasi yang memiliki data koordinat sebagai marker berlambang 🏛. Warna lingkaran marker menunjukkan status: HIJAU = Aktif, MERAH = Tidak Aktif. Arahkan kursor ke marker untuk melihat nama koperasi, dan klik marker untuk membuka Panel Info detail.

Gambar: Area peta dengan marker koperasi se-Sulawesi Tenggara, kontrol layer basemap (kiri bawah), dan tombol zoom (kanan bawah)

Fitur Peta	Cara Penggunaan
Zoom In/Out	Tombol +/− kanan bawah, atau scroll mouse
Geser Peta	Klik tahan dan seret area peta
Ganti Basemap	Klik kontrol layer kiri bawah → pilih: OpenStreetMap, Google Satellite, Google Terrain, atau ESRI
Batas Wilayah	Aktifkan layer 'Batas Wilayah (Kecamatan)' di kontrol layer
Lokasi Saya	Klik tombol crosshair (◎) di kiri atas peta
Fit ke Semua Marker	Otomatis saat data dimuat, atau reset filter wilayah

3.2 Panel Info Koperasi

Klik marker atau baris tabel untuk membuka Panel Info di sudut kanan atas peta. Panel menampilkan detail lengkap koperasi beserta foto, status, NIK, pengurus, anggota, gerai, kesehatan, dan tautan Google Maps.

Gambar: Panel Info detail koperasi (KSP Sejahtera Mandiri)



Gambar: Baris pencarian dan filter tabel data

Tombol di Panel Info	Fungsi
✎ (Pensil)	Mode Edit data koperasi — hanya tampil saat login Admin
∨ (Chevron)	Ciutkan / luaskan panel info
✕ (Silang)	Tutup panel info

3.3 Filter & Pencarian Data

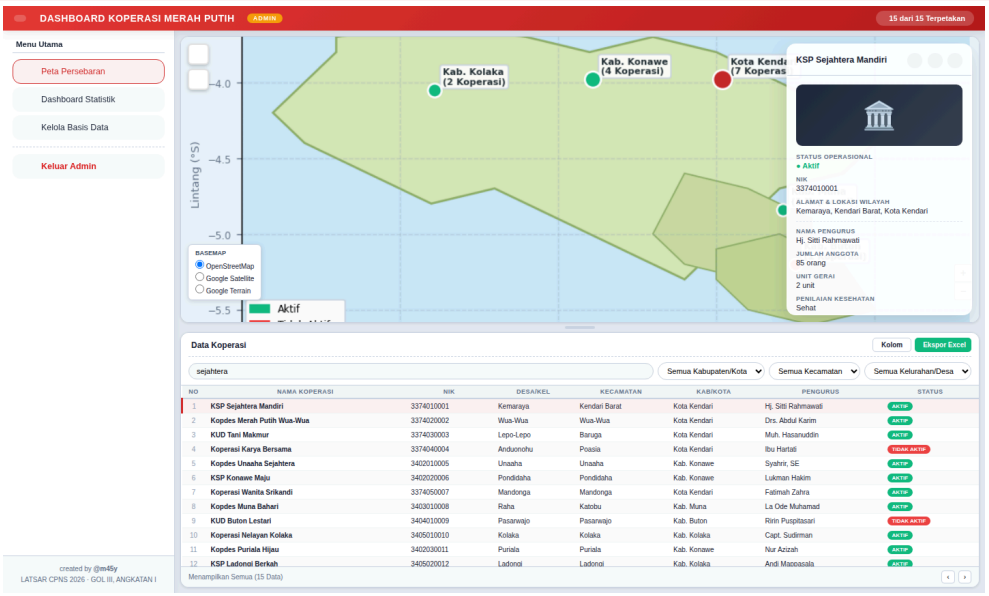

Gambar: Contoh pencarian teks: ketik "sejahtera" — tabel dan peta memperbarui hasil secara real-time

Filter	Cara Penggunaan
Kotak Teks	Ketik nama koperasi, desa, NIK, atau pengurus
Dropdown Kabupaten/Kota	Persempit ke satu kabupaten; peta otomatis zoom ke area
Dropdown Kecamatan	Aktif setelah memilih kabupaten
Dropdown Desa/Kel	Aktif setelah memilih kecamatan
Filter Kategori	Klik 'Kategori' → filter Status, Unit Gerai, Kesehatan

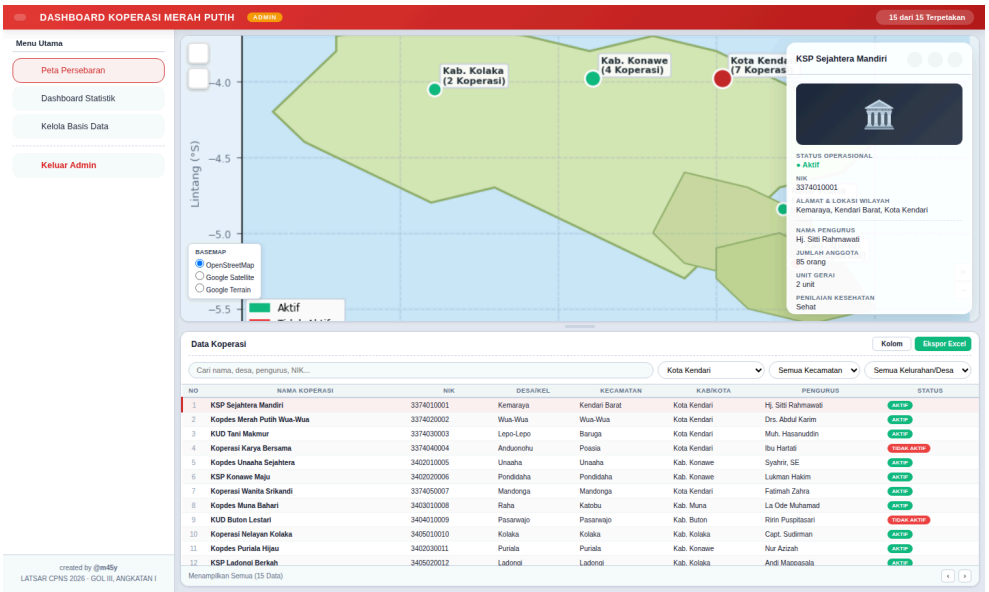

Gambar: Filter aktif "Kota Kendari": peta zoom ke Kota Kendari, tabel menampilkan 7 koperasi Kota Kendari

3.4 Tabel Data Koperasi

Data Koperasi

Kolom | Ekspor Excel

Cari nama, desa, pengurus, NIK... | Semua Kabupaten/Kota | Semua Kecamatan | Semua Kelurahan/Desa

NO	NAMA KOPERASI	NIK	DESA/KEL	KECAMATAN	KAB/KOTA	PENGURUS	STATUS
1	KSP Sejahtera Mandiri	3374010001	Kemaraya	Kendari Barat	Kota Kendari	Hj. Sitti Rahmawati	AKTIF
2	Kopdes Merah Putih Wua-Wua	3374020002	Wua-Wua	Wua-Wua	Kota Kendari	Drs. Abdul Karim	AKTIF
3	KUD Tani Makmur	3374030003	Lepo-Lepo	Baruga	Kota Kendari	Muh. Hasanuddin	AKTIF
4	Koperasi Karya Bersama	3374040004	Anduonohu	Poasia	Kota Kendari	Ibu Hartati	TIDAK AKTIF
5	Kopdes Unaaha Sejahtera	3402010005	Unaaha	Unaaha	Kab. Konawe	Syahrir, SE	AKTIF
6	KSP Konawe Maju	3402020006	Pondidaha	Pondidaha	Kab. Konawe	Lukman Hakim	AKTIF
7	Koperasi Wanita Srikandi	3374050007	Mandonga	Mandonga	Kota Kendari	Fatimah Zahra	AKTIF
8	Kopdes Muna Bahari	3403010008	Raha	Katobu	Kab. Muna	La Ode Muhamad	AKTIF
9	KUD Buton Lestari	3404010009	Pasarwajo	Pasarwajo	Kab. Buton	Ririn Puspitasari	TIDAK AKTIF
10	Koperasi Nelayan Kolaka	3405010010	Kolaka	Kolaka	Kab. Kolaka	Capt. Sudirman	AKTIF
11	Kopdes Puriala Hijau	3402030011	Puriala	Puriala	Kab. Konawe	Nur Azizah	AKTIF
12	KSP Ladongi Berkah	3405020012	Ladongi	Ladongi	Kab. Kolaka	Andi Mappasala	AKTIF

Menampilkan Semua (15 Data)

Gambar: Tabel data lengkap 15 koperasi: baris pertama (KSP Sejahtera Mandiri) terpilih dengan highlight merah

Fitur tabel: klik judul kolom untuk mengurutkan, tombol 'Kolom' untuk atur tampilan dan urutan kolom (drag & drop), dan tombol hijau 'Ekspor Excel' untuk unduh data ke file .xlsx.

BAB 4 — Dashboard Statistik

4.1 Gambaran Umum

Halaman statistik menampilkan ringkasan data dalam bentuk kartu KPI dan tiga jenis grafik interaktif. Semua data diperbarui secara otomatis mengikuti filter wilayah yang dipilih.

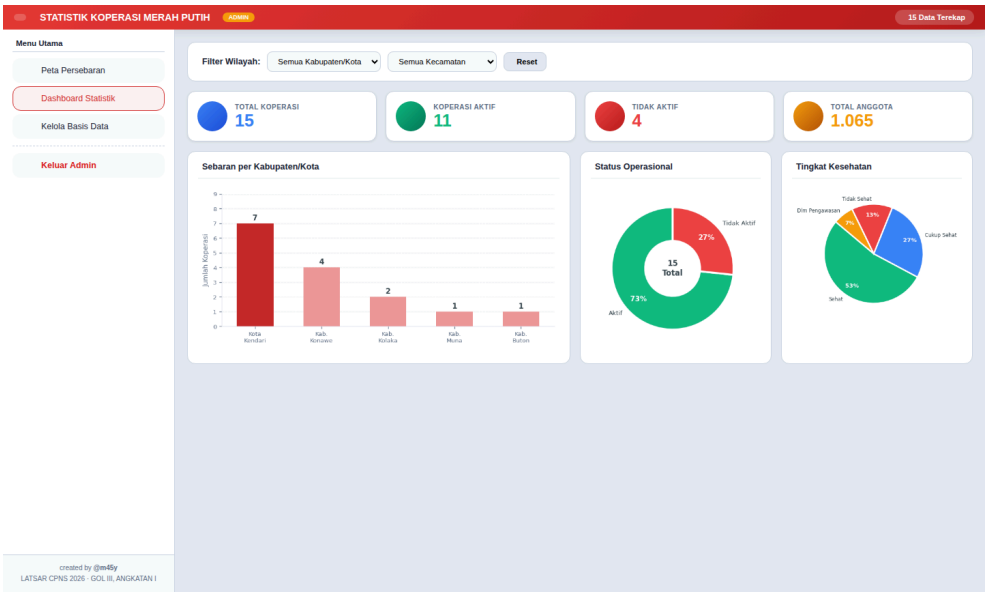

Gambar: Dashboard Statistik lengkap: filter wilayah, 4 kartu KPI, grafik batang sebaran, donat status, dan pie kesehatan

4.2 Kartu KPI

Gambar: 4 Kartu KPI: Total Koperasi (15), Koperasi Aktif (11), Tidak Aktif (4), Total Anggota (1.065)

Kartu KPI	Keterangan
Total Koperasi (Biru)	Jumlah total sesuai filter aktif
Koperasi Aktif (Hijau)	Koperasi berstatus Aktif
Tidak Aktif (Merah)	Koperasi berstatus Tidak Aktif
Total Anggota (Oranye)	Akumulasi jumlah anggota seluruh koperasi

4.3 Grafik Visualisasi

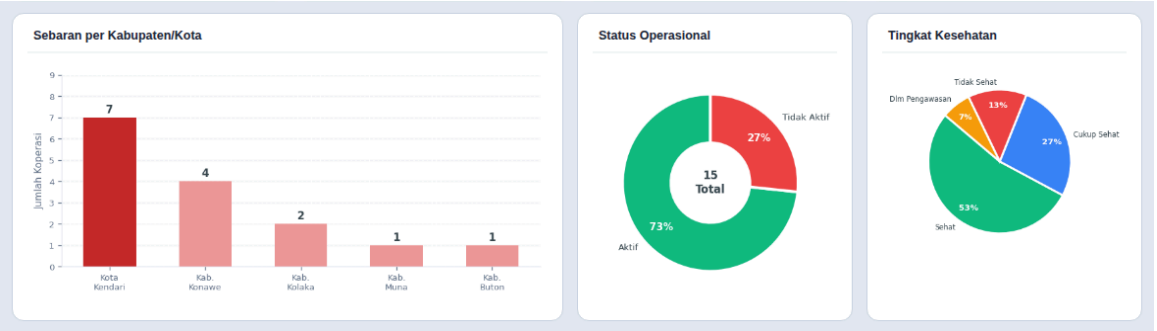

Gambar: Tiga grafik: (1) Batang sebaran per Kab/Kota, (2) Donat status operasional, (3) Pie tingkat kesehatan

Grafik	Deskripsi
Batang Wilayah	Jumlah koperasi per Kab/Kota. Saat filter Kabupaten aktif → berubah ke per Kecamatan
Donat Status	Proporsi Aktif vs Tidak Aktif, angka total di tengah
Pie Kesehatan	Distribusi berdasarkan Sehat, Cukup Sehat, Tidak Sehat, Dalam Pengawasan

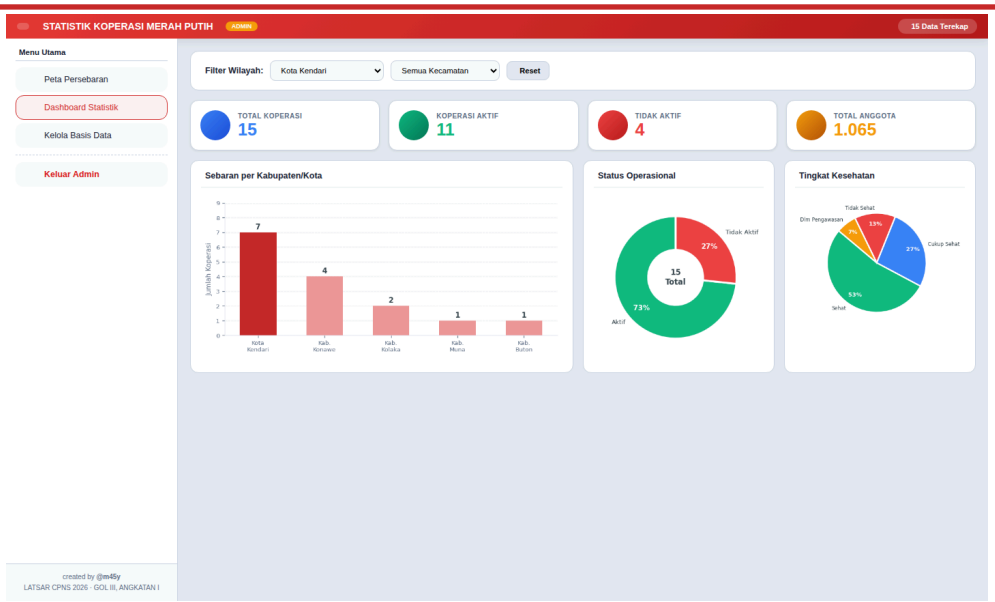

Gambar: Filter "Kota Kendari" aktif: KPI dan grafik diperbarui menampilkan data 7 koperasi Kota Kendari

BAB 5 — Login Administrator

5.1 Tampilan Halaman Login

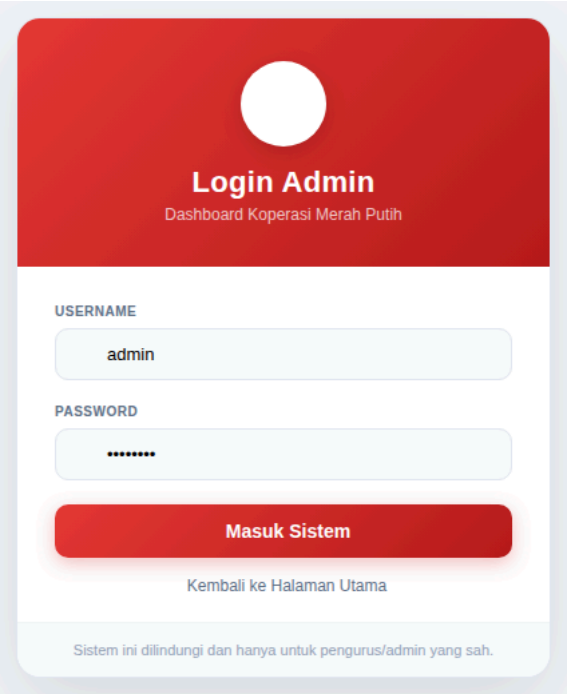

Gambar: Tampilan halaman login.html — form autentikasi admin

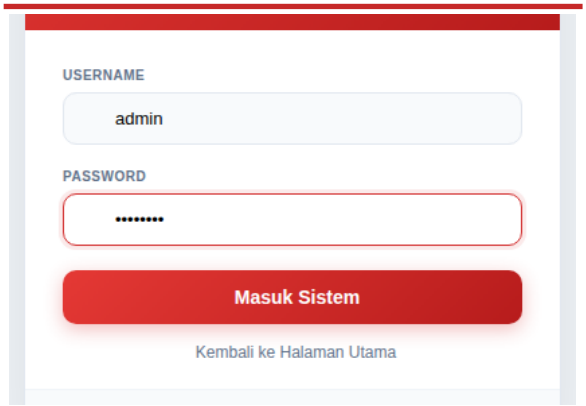

Gambar: Field Username & Password saat diisi — tombol Masuk Sistem aktif

5.2 Cara Login

1	Klik menu 'Login Admin' di sidebar navigasi halaman mana pun.
2	Anda diarahkan ke halaman login.html.
3	Masukkan Username dan Password yang valid.
4	Klik tombol 'Masuk Sistem' (merah).
5	Notifikasi sukses tampil → sistem redirect ke index.html mode Admin.

5.3 Indikator Mode Admin Aktif

- Badge 'ADMIN' oranye muncul di header di sebelah nama aplikasi.
- Menu 'Kelola Basis Data' muncul di sidebar.
- Ikon pensil (✎ Edit) muncul di Panel Info saat koperasi dipilih.
- Tombol satelit (cek GPS akurasi tinggi) muncul di atas peta.

- Menu 'Login Admin' berganti menjadi 'Keluar Admin' di sidebar.

INFO

Status login tersimpan di localStorage browser. Tetap aktif hingga klik 'Keluar Admin' atau sesi browser dihapus.

BAB 6 — Kelola Basis Data

6.1 Tampilan Halaman

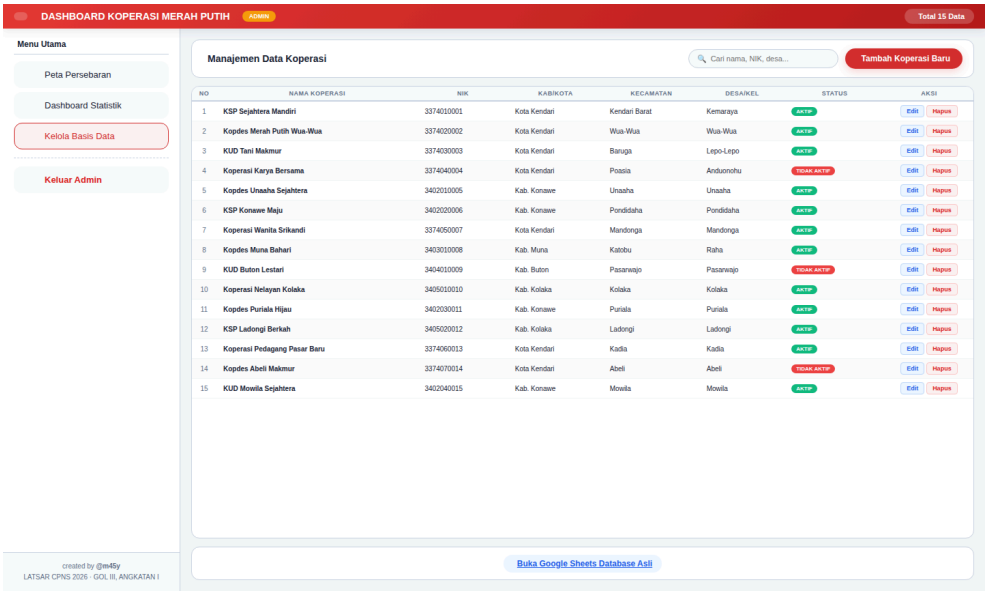

Gambar: Halaman database.html: topbar dengan tombol Tambah dan pencarian, tabel manajemen dengan tombol Edit & Hapus per baris

6.2 Pencarian Data

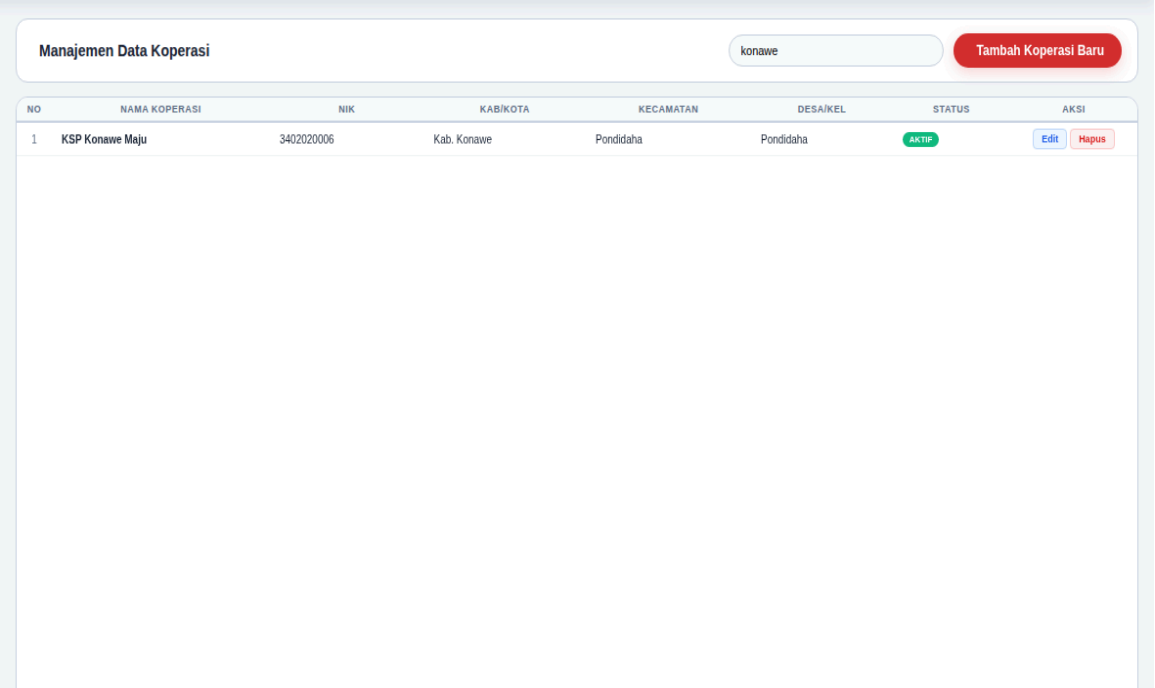

Gambar: Pencarian "konawe": tabel memfilter real-time menampilkan 4 koperasi Kabupaten Konawe

6.3 Form Tambah / Edit Data

Klik '+ Tambah Koperasi Baru' atau tombol 'Edit' untuk membuka form modal pop-up. Form dibagi tiga bagian: Informasi Utama, Informasi Tambahan, dan Titik Koordinat.

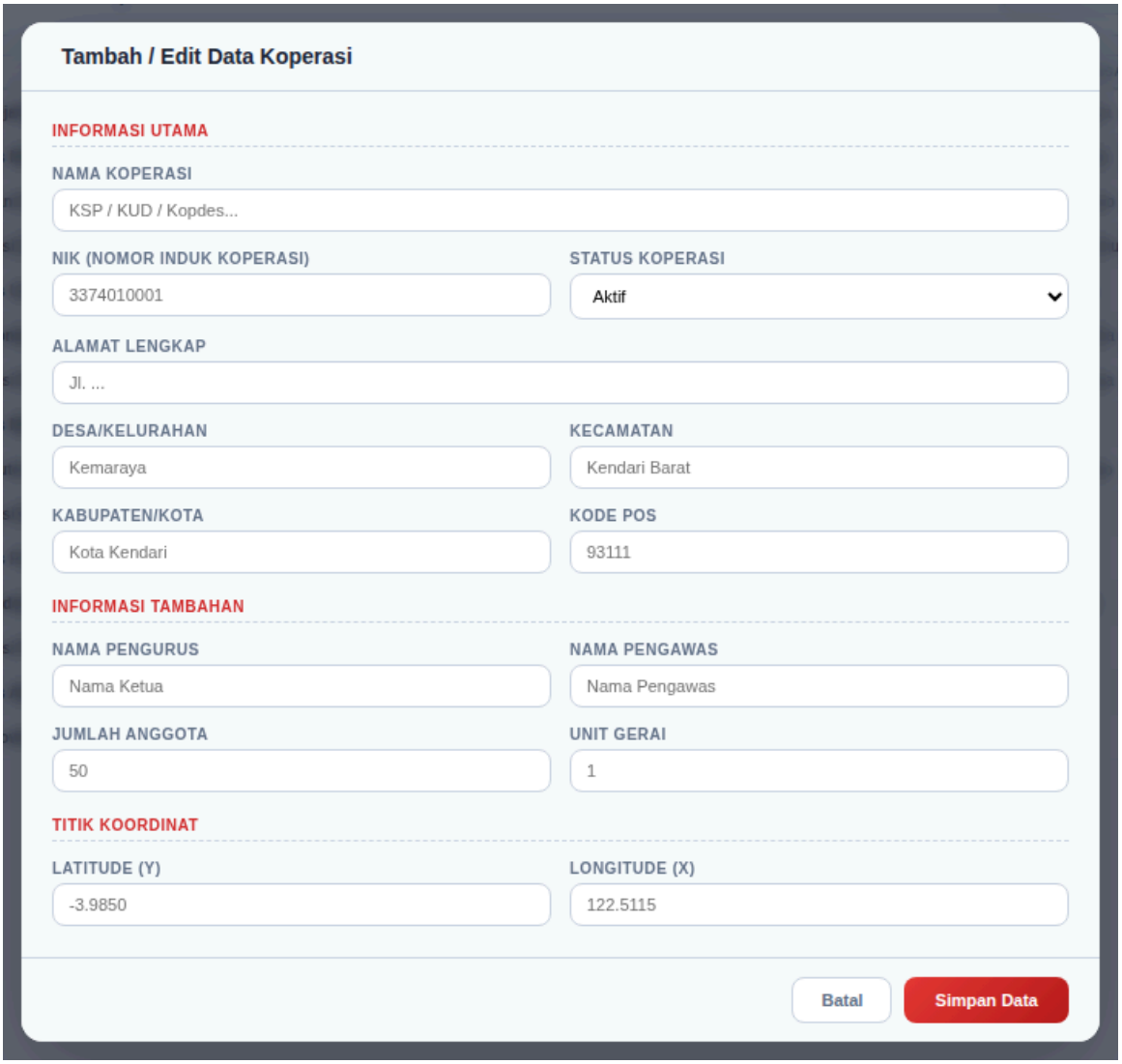

Gambar: Form modal Tambah/Edit: Informasi Utama (nama, NIK, status, alamat, wilayah, kode pos), Informasi Tambahan (pengurus, pengawas, anggota, gerai), dan Titik Koordinat (lat/lng)

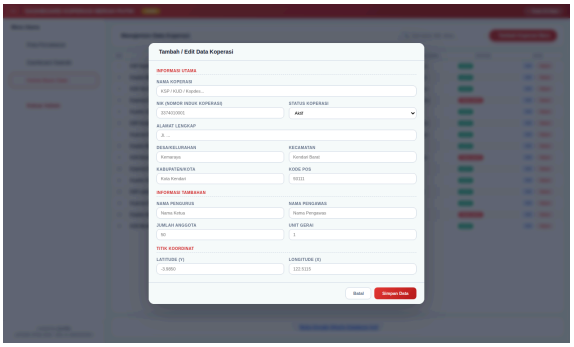

Gambar: Modal Tambah terbuka di atas halaman basis data

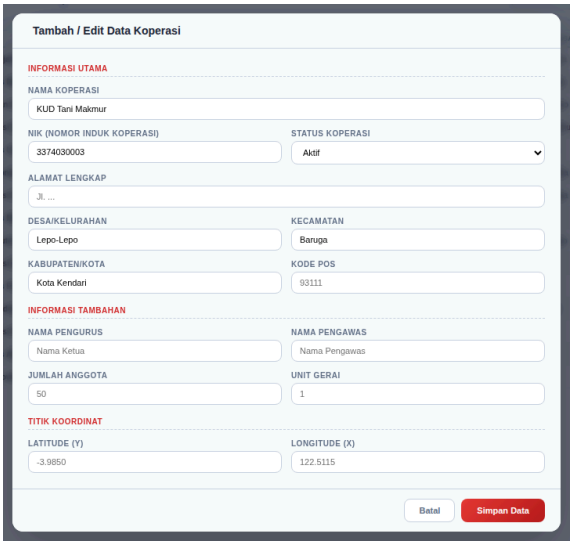

Gambar: Modal Edit dengan data koperasi yang sudah terisi

6.4 Langkah Tambah Koperasi Baru

1	Klik tombol merah '+ Tambah Koperasi Baru' di bagian atas halaman.
2	Form modal terbuka dengan kolom kosong.
3	Isi Nama Koperasi, NIK, Status, Alamat, Desa, Kecamatan, Kab/Kota, dan Kode Pos.
4	Isi Pengurus, Pengawas, Jumlah Anggota, dan Unit Gerai.
5	Masukkan koordinat (Latitude/Longitude) secara manual, atau klik mini-peta dalam form.
6	Upload foto: pilih file → klik 'Unggah', URL otomatis terisi.
7	Klik 'Simpan Data' — tersimpan langsung ke Google Sheets.

PERHATIAN

Penghapusan data bersifat permanen. Klik tombol merah 'Hapus' → konfirmasi dialog → data hilang dari sistem.

BAB 7 — Sinkronisasi API Kemenkop

7.1 Gambaran Umum

Fitur sinkronisasi memungkinkan admin menarik 5 data otomatis dari sistem nasional Kemenkop (merahputih.kop.id): Kode Pos, Pengurus, Pengawas, Jumlah Anggota, dan Unit Gerai.

7.2 Cara Sinkronisasi

1. Di halaman Kelola Basis Data, cari koperasi yang ingin disinkronkan.
2. Klik nama koperasi yang bergaris bawah (koperasi harus punya URL sistem di kolom URL).
3. Modal Viewer API terbuka — data ditarik otomatis dari server Kemenkop.
4. Periksa data: info utama, foto koperasi, peta lokasi koordinat, tabel pengurus/anggota/outlet.
5. Klik tombol hijau 'Gunakan Data Ini ke Form'.
6. Form edit terbuka — 5 field sudah terisi otomatis.
7. Cek, perbaiki jika perlu, lalu klik 'Simpan Data'.

Field Lokal	Sumber dari API Kemenkop
Kode Pos	Field postal_code
Nama Pengurus	Daftar managements dengan status PENGURUS
Nama Pengawas	Daftar managements dengan status PENGAWAS
Jumlah Anggota	Dihitung dari jumlah entri di daftar members
Unit Gerai	Dihitung dari jumlah entri di daftar outlets

BAB 8 — Tips & Troubleshooting

8.1 Masalah Umum & Solusi

Masalah	Solusi
Data tidak muncul / loading lama	Periksa koneksi internet. Klik area statistik di header → 'Sinkronisasi'.
Peta tidak tampil	Refresh halaman. Tile peta memerlukan koneksi internet ke server eksternal.
Login gagal	Pastikan username/password benar. Hubungi admin sistem jika lupa.
Foto tidak tampil	URL foto tidak valid atau akses Google Drive dibatasi. Gunakan tombol 'Unggah' di form.
API Kemenkop gagal	Perlu koneksi stabil. Pastikan koperasi punya URL sistem yang valid.
database.html tidak bisa dibuka	Harus login Admin terlebih dahulu. Sistem otomatis redirect ke halaman login.
Export Excel tidak berfungsi	Tunggu data selesai dimuat sebelum ekspor. Coba lagi setelah refresh.
Koordinat tidak akurat saat klik peta	Zoom peta lebih dekat ke lokasi sebelum klik untuk presisi lebih tinggi.

8.2 Tips Penggunaan Optimal

- Filter wilayah sebelum ekspor Excel agar file hanya berisi data yang relevan.
- Aktifkan layer 'Batas Wilayah (Kecamatan)' di kontrol layer peta untuk identifikasi area lebih jelas.
- Gunakan tombol satelit (Admin) untuk mendapatkan koordinat GPS presisi tinggi saat input lokasi baru.
- Label nama koperasi muncul otomatis saat zoom > 13.5 — zoom keluar untuk menyembunyikannya.
- Di perangkat mobile: sidebar otomatis jadi overlay — gunakan tombol ≡ untuk membuka/menutupnya.
- Seret pembatas (resizer) antara peta dan tabel untuk menyesuaikan proporsi tampilan sesuai kebutuhan.

Dashboard Koperasi Desa/Kelurahan Merah Putih Sulawesi Tenggara

Dibuat oleh @m45y · LATSAR CPNS 2026 · GOL III, ANGKATAN I