BUKU PANDUAN PENGGUNAAN

Dashboard Koperasi

Desa/Kelurahan Merah Putih

Sulawesi Tenggara

https://koperasi-sultra.vercel.app

Daftar Isi

Apa saja yang akan dibahas?

01 **Tentang Aplikasi**
Tujuan, pengguna, teknologi

02 **Navigasi Umum**
Layout, sidebar, header

03 **Peta Persebaran**
Marker, filter, tabel

04 **Panel Info**
Detail koperasi, foto

05 **Dashboard Statistik**
KPI, grafik, filter

06 **Login Admin**
Autentikasi & hak akses

07 **Kelola Basis Data**
Tambah, edit, hapus

08 **Sinkronisasi API**
Integrasi Kemenkop

09 **Tips & Troubleshooting**
Solusi masalah umum

01

Tentang Aplikasi

Tujuan, pengguna, dan teknologi yang digunakan

Apa itu Dashboard Koperasi Merah Putih?

Aplikasi web untuk memetakan, memantau, dan mengelola data koperasi desa/kelurahan di Sulawesi Tenggara, terintegrasi dengan Google Sheets dan API Kemenkop.

Peta Interaktif

Visualisasi sebaran geografis koperasi

Dashboard Statistik

KPI & grafik analisis data koperasi

Manajemen Data

CRUD data terintegrasi Google Sheets

Sinkronisasi API

Integrasi real-time dengan Kemenkop

Jenis Pengguna

Pengguna Umum (Guest)

Lihat peta, statistik, export Excel

Administrator

Semua akses + edit/hapus/tambah data, sinkronisasi API

Teknologi yang Digunakan

- Peta Interaktif → Leaflet.js + OpenStreetMap
- Grafik & Chart → Chart.js
- Basis Data → Google Sheets / Apps Script
- Export Excel → SheetJS (XLSX)
- UI Framework → Tailwind CSS
- Notifikasi → SweetAlert2
- Drag & Drop → SortableJS
- API Sinkronisasi → Kemenkop (merahputih.kop.id)

02

Navigasi Umum

Layout, sidebar, header, dan struktur halaman

Struktur tata letak (layout) aplikasi

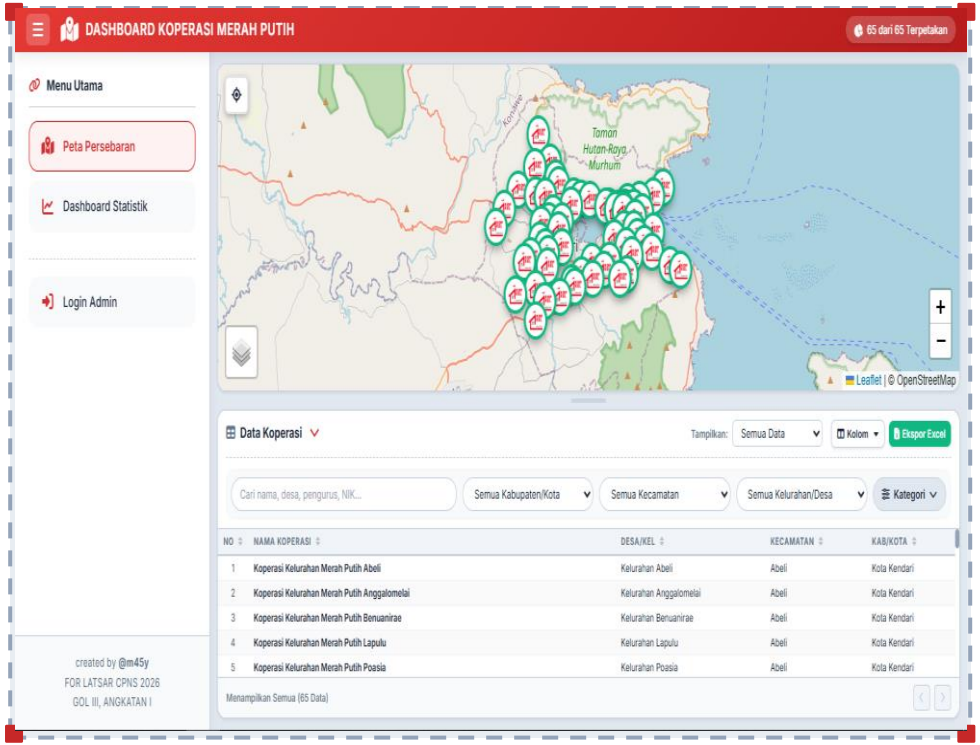

Header

Logo, nama app, badge Admin, tombol refresh/statistik

Sidebar Kiri

Menu navigasi: Peta, Statistik, Basis Data, Login/Logout

Area Konten

Peta interaktif + tabel data koperasi

Tombol ≡

Buka/tutup sidebar (hamburger menu)

4 Halaman Utama:

1. index.html — Peta Persebaran
2. statistik.html — Dashboard Statistik
3. database.html — Kelola Basis Data (Admin)
4. login.html — Login Administrator

03

Halaman Peta Persebaran

index.html — Fitur peta interaktif dan tabel data

Komponen utama halaman Peta Persebaran

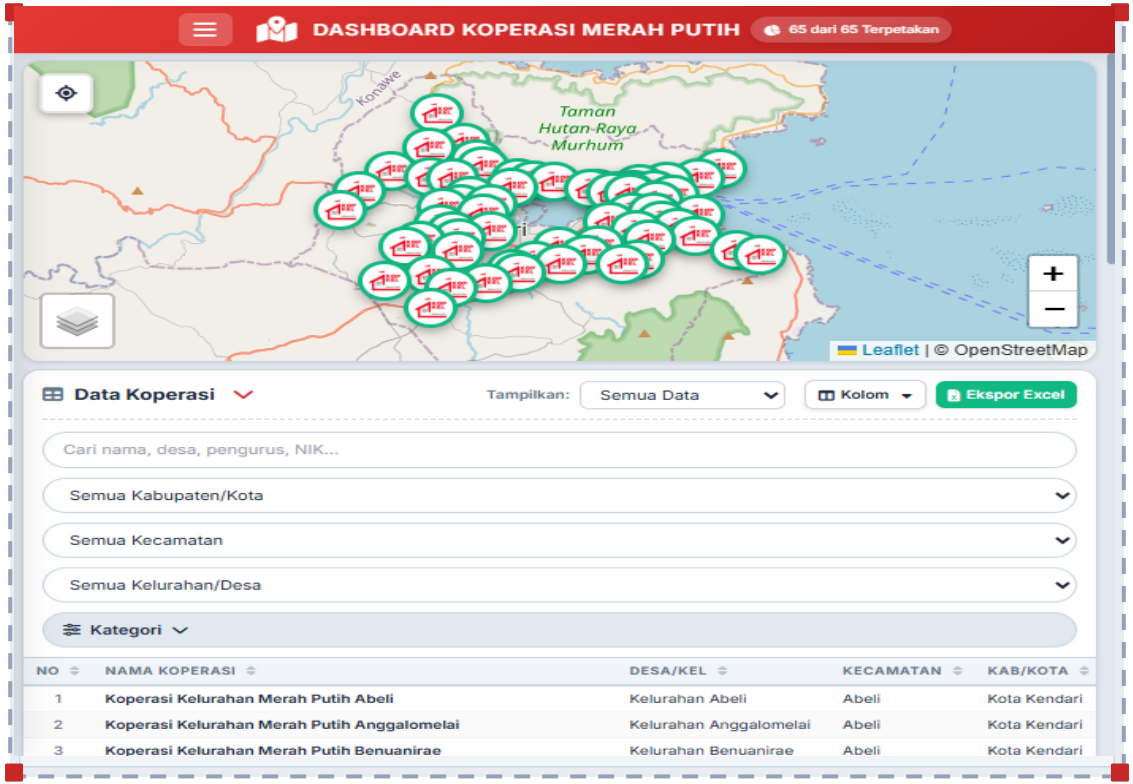

A — **Peta Interaktif**
Area peta utama dengan marker koperasi

B — **Floating Buttons**
Tombol lokasi saya & cek GPS (Admin)

C — **Panel Info**
Detail koperasi saat marker diklik

D — **Tabel Data**
Daftar koperasi + filter + pencarian

E — **Resizer**
Geser untuk ubah proporsi peta/tabel

Jenis marker dan pilihan basemap yang tersedia

Marker Koperasi di Peta

Lingkaran HIJAU

Koperasi berstatus Aktif

Lingkaran MERAH

Koperasi berstatus Tidak Aktif



Pilihan Basemap

Open Street Map

Default — Peta jalan detail

Google Satellite

Citra satelit resolusi tinggi

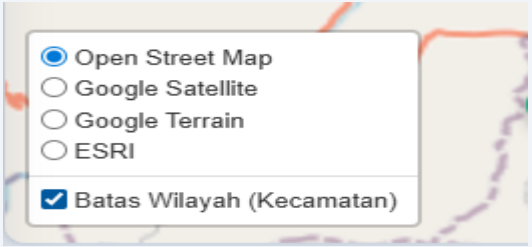

Cara memfilter dan mencari data koperasi di tabel

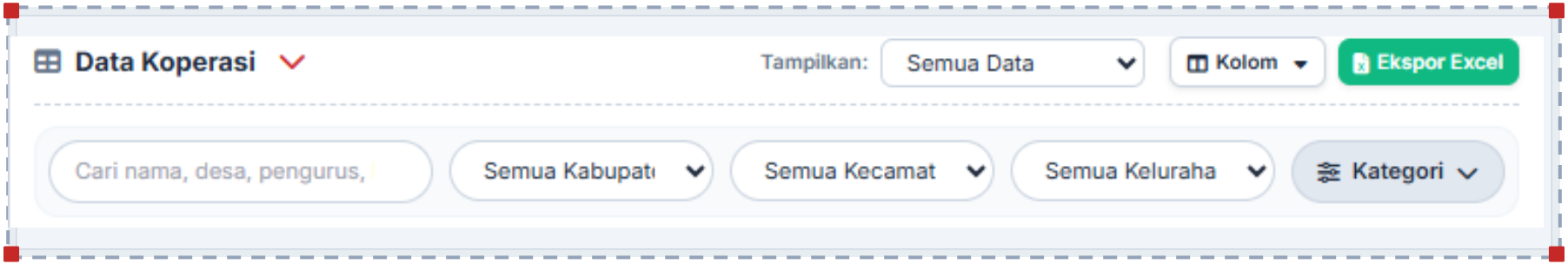

Kotak Pencarian Teks

Cari berdasarkan nama koperasi, desa, NIK, atau pengurus

Dropdown Desa/Kelurahan

Aktif setelah memilih Kecamatan.

Dropdown Kabupaten/Kota

Persempit tampilan ke satu kabupaten. Peta otomatis zoom ke area tersebut.

Filter Kategori (Lanjutan)

Filter berdasarkan Status Operasional, Unit Gerai, atau Tingkat Kesehatan

Dropdown Kecamatan

Aktif setelah memilih Kabupaten. Batas kecamatan tampil di peta.

Mengatur tampilan kolom dan mengekspor data

Mengatur Kolom Tabel

1. Klik tombol 'Kolom' di area kontrol tabel
2. Menu popup daftar kolom akan terbuka
3. ✓ Centang kolom yang ingin ditampilkan
4. ✗ Hapus centang untuk menyembunyikan kolom
5. ⠿ Seret (drag) handle ⠿ untuk ubah urutan kolom

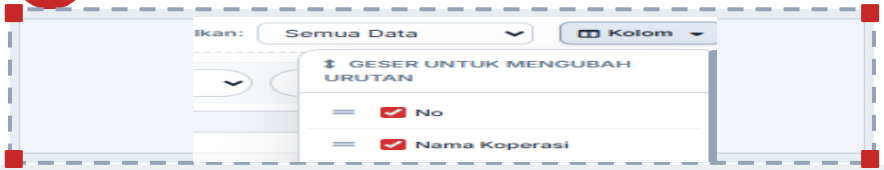

Ekspor Data ke Excel

Tombol 'Ekspor Excel'

Klik tombol hijau 'Ekspor Excel' untuk mengunduh semua data yang saat ini ditampilkan/difilter ke dalam file .xlsx.

Tips

Filter data terlebih dahulu sebelum ekspor agar file Excel hanya berisi data yang relevan untuk kebutuhan laporan Anda.

04

Panel Info Koperasi

Detail koperasi, foto, dan navigasi Google Maps

Panel detail muncul saat marker atau baris tabel diklik

Kontrol Panel

Tombol Edit (Pensil)
Masuk Mode Edit data (Admin only)

Tombol Minimize
Ciutkan/luaskan panel info

Tombol Tutup
Tutup panel info koperasi

Panel menampilkan:

- Foto slider koperasi (klik foto = fullscreen)
- Status operasional, alamat, wilayah
- NIK, SK AHU, Jenis, Pengurus, Pengawas
- Jumlah anggota, sektor usaha, gerai, kesehatan
- Tautan Rute Google Maps (jika ada koordinat)

05

Dashboard Statistik

statistik.html — KPI, grafik, dan filter wilayah

Visualisasi data koperasi dalam grafik dan kartu KPI

4 Kartu KPI:

99

Total Koperasi

Jumlah total koperasi sesuai filter aktif

99

Koperasi Aktif

Koperasi dengan status Aktif

99

Tidak Aktif

Koperasi dengan status Tidak Aktif

99

Telah RAT

RAT pada tahun terakhir / berjalan

Tiga jenis grafik tersedia, semuanya responsif terhadap filter wilayah

Grafik Batang Wilayah

Sebaran koperasi per Kabupaten/Kota. Jika filter Kabupaten aktif → berubah ke sebaran per Kecamatan.

Grafik Donat Status

Proporsi koperasi Aktif vs Tidak Aktif.

Grafik Pie Kesehatan

Distribusi koperasi berdasarkan kategori penilaian kesehatan.

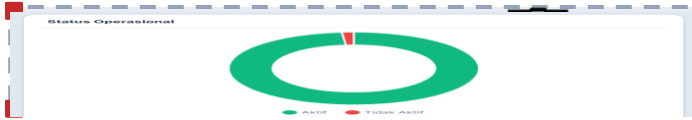

Filter Wilayah

1. Pilih Kabupaten/Kota dari dropdown
2. Pilih Kecamatan (opsional)
3. Semua KPI & grafik otomatis diperbarui
4. Klik tombol 'Reset' untuk hapus filter

💡 Angka KPI menggunakan animasi counter saat diperbarui.

06

Login Administrator

login.html — Autentikasi dan hak akses admin

Panduan langkah demi langkah untuk login admin

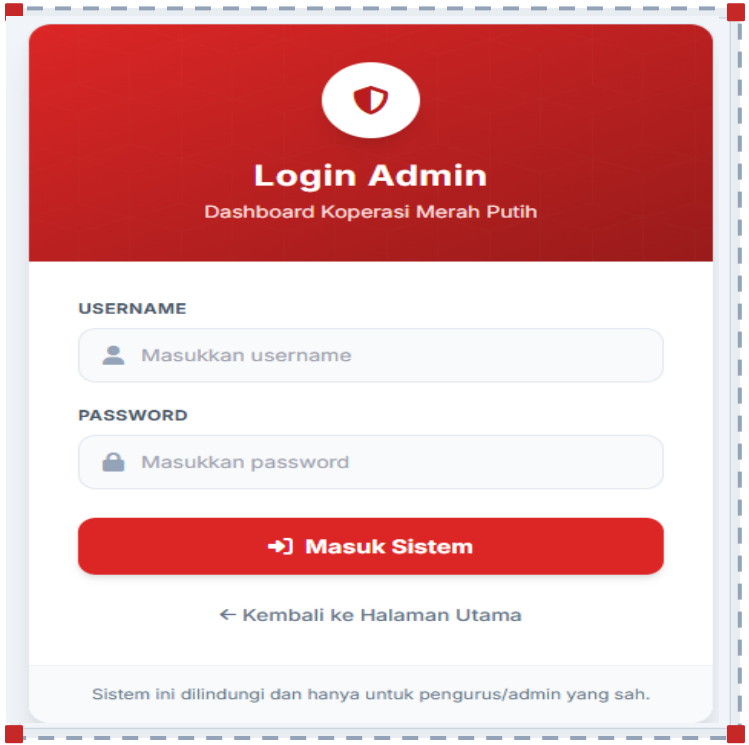

Langkah Login:

1. Klik menu 'Login Admin' di sidebar
2. Anda diarahkan ke halaman login.html
3. Masukkan Username dan Password
4. Klik tombol 'Masuk Sistem'
5. Notifikasi sukses → redirect ke index.html

Indikator Mode Admin aktif:

- Badge 'ADMIN' oranye di header
- Menu 'Kelola Basis Data' muncul di sidebar
- Ikon edit (pensil) di Panel Info koperasi
- Tombol cek GPS akurasi tinggi di peta

07

Kelola Basis Data

database.html — Tambah, edit, hapus, & upload foto

Manajemen data koperasi secara terpusat (khusus Admin)

NO	NAMA KOPERASI	NIK	KAB/KOTA	KECAMATAN	DESA/KEL	STATUS	AKSI
1	Koperasi Kelurahan Merah Putih Abeli	7471050080032	Kota Kendari	Abeli	Kelurahan Abeli	AKTIF	Edit Hapus
2	Koperasi Kelurahan Merah Putih Anggalomelai	7471050060002	Kota Kendari	Abeli	Kelurahan Anggalomelai	AKTIF	Edit Hapus
3	Koperasi Kelurahan Merah Putih Benuanirae	7471050090001	Kota Kendari	Abeli	Kelurahan Benuanirae	AKTIF	Edit Hapus
4	Koperasi Kelurahan Merah Putih Lapulu	7471050120030	Kota Kendari	Abeli	Kelurahan Lapulu	AKTIF	Edit Hapus
5	Koperasi Kelurahan Merah Putih Poasia	7471050110016	Kota Kendari	Abeli	Kelurahan Poasia	AKTIF	Edit Hapus
6	Koperasi Kelurahan Merah Putih Puday	7471050130031	Kota Kendari	Abeli	Kelurahan Puday	AKTIF	Edit Hapus

+ Tambah Baru

Klik tombol merah '+ Tambah Koperasi Baru' di bagian atas

Hapus Data

Klik tombol merah 'Hapus', konfirmasi dialog hapus

Edit Data

Klik tombol biru 'Edit' pada baris koperasi di tabel

Cari Koperasi

Ketik di kotak pencarian: nama, NIK, desa, kecamatan

Modal form pop-up untuk menambah atau mengedit data koperasi

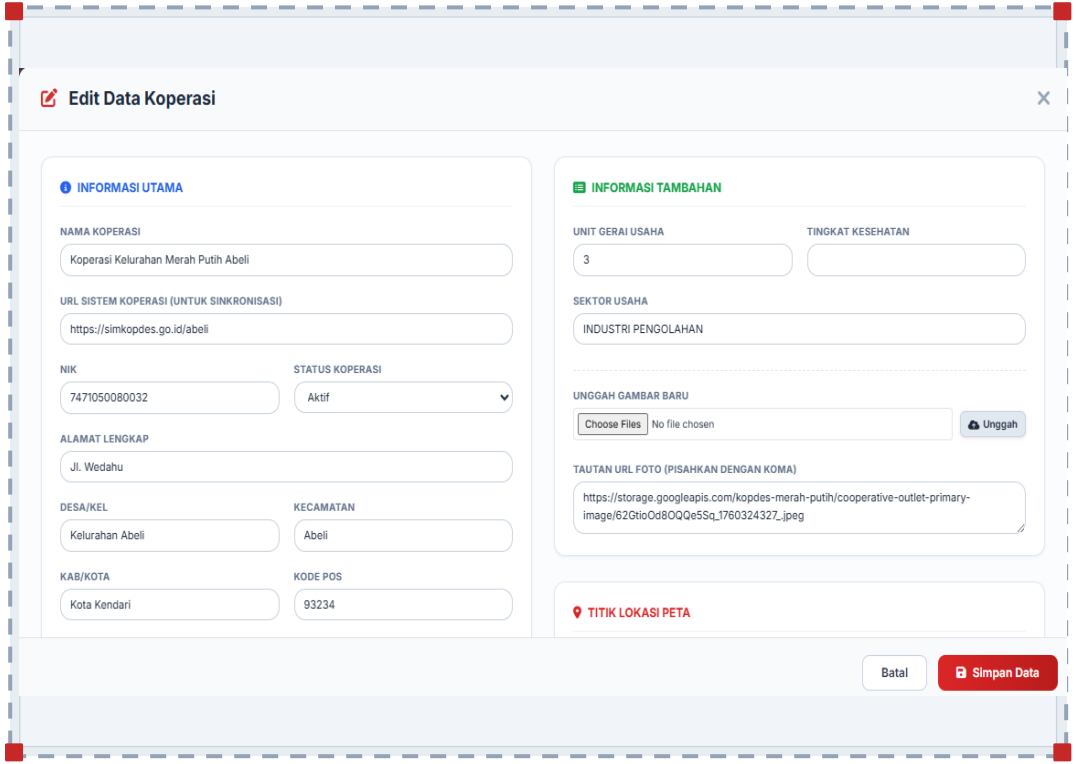

Informasi Utama

Nama, NIK, Status, URL, Alamat, Desa, Kecamatan, Kab/Kota, Kode Pos, SK AHU, Jenis, Th. Pendirian

Informasi Tambahan

Pengurus, Pengawas, Jumlah Anggota, Sektor Usaha, Unit Gerai, Tingkat Kesehatan

Titik Lokasi Peta

Latitude (Y) & Longitude (X) — isi manual atau klik mini-peta di form

Foto Koperasi

Upload file baru atau isi tautan URL foto (pisahkan dengan koma)

⚠ Hapus data bersifat permanen dan tidak dapat dibatalkan.

08

Sinkronisasi API Kemenkop

Menarik data otomatis dari sistem nasional Kemenkop

Tarik data terkini dari sistem Kemenkop dengan sekali klik

Langkah sinkronisasi:

1. Di tabel Kelola Basis Data, klik nama koperasi yang bergaris bawah
2. Modal Viewer API terbuka, data ditarik otomatis dari server Kemenkop
3. Periksa data: info utama, foto, peta lokasi, tabel manajemen/anggota/outlet
4. Klik tombol hijau 'Gunakan Data Ini ke Form'
5. Form edit terbuka — 5 field sudah terisi otomatis
6. Periksa dan simpan data

Data yang ditarik otomatis:

- ✓ **Kode Pos**
  Dari field postal_code API
- ✓ **Nama Pengurus**
  Managements dengan status PENGURUS
- ✓ **Nama Pengawas**
  Managements dengan status PENGAWAS
- ✓ **Jumlah Anggota**
  Dihitung dari jumlah entri members
- ✓ **Unit Gerai**
  Dihitung dari jumlah entri outlets

08 — Sinkronisasi Data dari API Kemenkop

Detail Data API Kemenkop

Tampilan data sinkronisasi dari pusat

KOPERASI KELURAHAN MERAH PUTIH ABELI

Abeli, Abeli, KOTA KENDARI, SULAWESI TENGGARA

Gunakan Data Ini ke Form

Informasi Utama

Nama Koperasi	KOPERASI KELURAHAN MERAH PUTIH ABELI
NIK	7471050080032
Alamat Lengkap	Jl. Wedahu
AHU	AHU-0066319.AH.01.29.TAHUN 2025
Tahun Pendirian	-
Kode Pos	93234
Jumlah Anggota	49
Pengurus	YESI RATNASARI, IDAYANTI, AFIANTI DAHLAN, MUHAMMAD NUR, LA ODE MUHAMMAD BIMA BHAKTI
Pengawas	ENDANG KRISNAWATI, H. MUHAMAD SYUKUR, S.E., M.Si., BAHARUDDIN

Informasi Tambahan

RAT	-
Unit Gerai Usaha	3
Penilaian Kesehatan	-
Sektor Usaha	Gerai Sembako (Embrio KopHub), Usaha Lainnya (KBLI 2020), Apotek Desa, Gerai Klinik Desa, Gerai Unit Usaha Simpan Pinjam (Embrio Kop Bank), Gerai Cold Storage/Cold Chain

Peta Lokasi

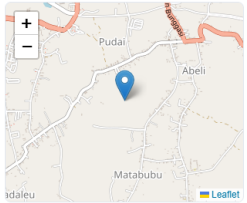

Koordinat: -3.998702, 122.577958

Detail Data API Kemenkop

Tampilan data sinkronisasi dari pusat

Gambar Koperasi

Logo Koperasi

Banner

Outlet #1 - Utama

Outlet #1 - Alternatif

Outle

Wilayah Administratif

PROVINSI	
Name	SULAWESI TENGGARA
Code	74

KABUPATEN/KOTA	
Name	KOTA KENDARI
Code	74.71

KECAMATAN	
Name	Abeli
Code	74.71.06
Subdistrict_id	5672

DESA/KELURAHAN	
Village_id	60612
Subdistrict_code	74.71.06
Code	74.71.06.1003
Name	Abeli
Created_at	-

Managements (Pengurus & Pengawas) 8 data

ROLE	NAME	STATUS	PROFILE_IMAGE	GENDER
KETUA	YESI RATNASARI	PENGURUS		PEREMPUAN
BENDAHARA	IDAYANTI	PENGURUS		PEREMPUAN
WAKIL KETUA BIDANG KEANGGOTAAN	AFIANTI DAHLAN	PENGURUS		PEREMPUAN

Members (Anggota) 49 data

NAME	NIK	GENDER	ROLE	POSITION	PHONE	MEMBER_IDENTIFICATION_NUMBER
RINA HASAN	7471066012850001	PEREMPUAN	ANGGOTA	ANGGOTA	6289526041804	7471066012850001
ANING NURNA NINGSIH	7471065803760001	PEREMPUAN	ANGGOTA	ANGGOTA	6281241196866	7471065803760001
HENDRI	7309012002770003	LAKI-LAKI	ANGGOTA	ANGGOTA	6285271727950	7309012002770003
RISNAWATI	7471064107740008	PEREMPUAN	ANGGOTA	ANGGOTA	6282244776378	7471064107740008
RUSNIA	7471065504820001	PEREMPUAN	ANGGOTA	ANGGOTA	6285396464180	7471065504820001
YOHANA SOFIA	7471045111810002	PEREMPUAN	ANGGOTA	ANGGOTA	6285145204771	7471045111810002
SITI HADNAN	7471066010780002	PEREMPUAN	ANGGOTA	ANGGOTA	6281244913573	7471066010780002
ENDANG KRISNAWATI	7471066305840001	PEREMPUAN	ANGGOTA	ANGGOTA	6282193100073	7471066305840001
ANWAR	7401011103920001	LAKI-LAKI	ANGGOTA	ANGGOTA	628114058723	747105008003200002

Members (Anggota) 49 data

Outlets (Gerai Usaha) 3 data

09

Tips & Troubleshooting

Solusi masalah umum dan tips penggunaan optimal

Temukan solusi cepat untuk kendala yang paling sering ditemui

❓ Data tidak muncul / loading lama

✅ Periksa koneksi internet. Klik area statistik di header untuk memuat ulang data (Sinkronisasi).

❓ Foto koperasi tidak tampil

✅ URL foto tidak valid atau akses Google Drive dibatasi. Gunakan tombol 'Unggah' di form untuk foto baru.

❓ Peta tidak tampil

✅ Refresh halaman. Koneksi internet stabil diperlukan karena tile peta dimuat dari server eksternal.

❓ Sinkronisasi API Kemenkop gagal

✅ Perlu koneksi stabil. Pastikan koperasi memiliki URL sistem yang valid di field URL.

❓ Login gagal

✅ Pastikan username & password benar. Hubungi admin sistem jika lupa kredensial.

❓ Halaman database.html tidak bisa dibuka

✅ Anda harus login Admin terlebih dahulu. Sistem otomatis redirect ke halaman login.

Gunakan fitur-fitur ini untuk pengalaman terbaik

Filter dulu, Export kemudian

Gunakan filter wilayah/status sebelum export Excel agar file yang diunduh hanya berisi data yang relevan.

Aktifkan Layer Batas Wilayah

Layer 'Batas Wilayah (Kecamatan)' di kontrol layer peta membantu identifikasi area wilayah dengan lebih jelas.

Gunakan Resizer Peta/Tabel

Seret pembatas antara peta dan tabel untuk menyesuaikan proporsi sesuai kebutuhan (lebih banyak peta atau tabel).

Zoom sebelum klik koordinat

Saat Mode Edit, zoom peta lebih dekat ke lokasi sebelum klik untuk mendapatkan koordinat yang lebih presisi.

Responsif di Mobile

Sidebar akan otomatis menjadi overlay di layar kecil. Klik tombol ≡ untuk membuka/tutupnya.

Label otomatis di zoom tinggi

Nama koperasi akan muncul di atas marker saat zoom > 13.5. Zoom keluar untuk menyembunyikan label.

Terima Kasih!

Panduan lengkap juga tersedia dalam format
Buku Manual (pdf) yang dapat diunduh.

Pertanyaan & masukan dapat disampaikan kepada pengembang.